Università del Salento
Facoltà di Ingegneria
Corso di Laurea in Ingegneria dell'Informazione

ChillChain — Piattaforma IoT per il trasporto refrigerato condiviso

Matching domanda-offerta e rilevazione anomalie con LSTM Autoencoder

Relatore
Prof. Luigi Patrono

Tutor
Ing. Teodoro Montanaro

Studente
Antonio Bello
Mat. 20093232

Anno Accademico 2025–2026

Indice

1 Introduzione **4**

2 Analisi dei Requisiti **6**
2.1 Requisiti Funzionali 6
2.1.1 Gestione degli utenti e autenticazione 6
2.1.2 Gestione della flotta 6
2.1.3 Gestione dei viaggi e delle spedizioni 7
2.1.4 Ricerca e prenotazione delle spedizioni 7
2.1.5 Consultazione delle spedizioni del cliente 7
2.1.6 Monitoraggio telemetrico in tempo reale 7
2.1.7 Rilevazione delle anomalie 7
2.1.8 Gestione delle notifiche 8
2.1.9 Reportistica della flotta 8
2.2 Requisiti Non Funzionali 8
2.2.1 Usabilità 8
2.2.2 Sicurezza 9
2.2.3 Modularità e manutenibilità 9
2.2.4 Portabilità e riproducibilità del deployment 9

3 Stato dell'Arte **10**
3.1 Flock Freight – FlockDirect® Shared Truckload 10
3.2 Carrier Lynx Fleet – Piattaforma digitale per il monitoraggio della catena del freddo 11
3.3 Rilevazione anomalie su serie temporali IoT 11
3.4 Sintesi e posizionamento della soluzione proposta 12

4 Tecnologie Utilizzate **13**
4.1 Spring Boot 13
4.2 React e TypeScript 13
4.3 MQTT e Mosquitto 14
4.4 MongoDB 14

4.5 Python, FastAPI e PyTorch 14
4.6 Google Maps Platform 15
4.7 Docker e Docker Compose 16

5 Soluzione Proposta 17
5.1 Architettura del sistema 17
5.2 Gestione degli utenti e autenticazione 18
5.3 Gestione della flotta e dei viaggi 19
5.3.1 Aggiunta di un veicolo 19
5.3.2 Lista veicoli 20
5.3.3 Lista viaggi 20
5.4 Marketplace: ricerca dei viaggi disponibili e creazione della spedizione 20
5.4.1 Fase 1 — Ricerca dei veicoli disponibili per un nuovo viaggio 21
5.4.2 Fase 2 — Ricerca dei viaggi già programmati 21
5.4.3 Fase 3 — Validazione geografica dei viaggi già programmati 21
5.4.4 Fase 4 — Ricalcolo del percorso con waypoint 22
5.4.5 Fase 5 — Pricing con divisore esponenziale 22
5.4.6 Selezione e conferma della tratta 22
5.5 Consultazione delle spedizioni del cliente 22
5.6 Generazione dei dati telemetrici 23
5.7 Pipeline di anomaly detection 23
5.7.1 Addestramento del modello 23
5.7.2 Inferenza in tempo reale 24
5.7.3 Smoothing con contatori consecutivi 24
5.8 Gestione delle notifiche 25
5.9 Dashboard telemetrica e reportistica 25
5.9.1 Reportistica della flotta 25

6 Validazione Funzionale 27
6.1 Ambiente di test 27
6.2 Scenario di validazione 27
6.2.1 Fase 1 — Configurazione della flotta e creazione del tecnico (Amministratore) 28
6.2.2 Fase 2 — Registrazione e prima spedizione (Cliente A) 29
6.2.3 Fase 3 — Seconda spedizione: condivisione della tratta (Cliente B) 30
6.2.4 Fase 4 — Consultazione delle spedizioni (Clienti A e B) 30

6.2.5 Fase 5 — Visualizzazione dei viaggi programmati e avvio simulazione 31
6.2.6 Fase 6 — Rilevazione anomalia e notifica (Tecnico) . . 31
6.2.7 Fase 7 — Consultazione dei report (Tecnico) 32

7 Conclusioni e Sviluppi Futuri 39
7.1 Conclusioni 39
7.2 Sviluppi futuri 39
7.2.1 Ottimizzazione temporale e scheduling attivo 39
7.2.2 Scalabilità su piattaforme cloud 40
7.2.3 Miglioramento della sensibilità dell'anomaly detection . 40
7.2.4 Indicizzazione spaziale con PostGIS 40
7.2.5 Sistema di notifiche push per il tecnico 40

Capitolo 1

Introduzione

La gestione della catena del freddo rappresenta una delle sfide più critiche nel settore della logistica. Il trasporto di merci deperibili richiede il mantenimento rigoroso di condizioni ambientali controllate lungo l'intera filiera distributiva, dalla produzione alla consegna finale. Anche una breve deviazione dalla temperatura richiesta può compromettere irrimediabilmente la qualità e la sicurezza dei prodotti trasportati, con conseguenze economiche rilevanti e potenziali rischi per la salute pubblica.

A rendere il problema ancora più complesso contribuisce la frammentazione del mercato del trasporto refrigerato: da un lato, le aziende di trasporto gestiscono flotte di veicoli che spesso viaggiano con capacità parzialmente inutilizzata; dall'altro, i clienti che necessitano di spedire piccoli quantitativi si trovano costretti o a sostenere costi elevati per soluzioni FTL (*Full Truckload* ovvero il noleggio di un intero veicolo refrigerato) o a ricorrere a soluzioni LTL (*Less Than Truckload*, ovvero spedizioni che condividono il veicolo di trasporto con altri carichi e che vengono consolidate in centri di smistamento intermedi), che comportano molteplici passaggi in magazzino, tempi di consegna più lunghi e un rischio maggiore di rottura della catena del freddo.

Le soluzioni attualmente disponibili sul mercato affrontano questi problemi in modo parziale e disgiunto. Piattaforme come Flock Freight [2] hanno introdotto il concetto di *Shared Truckload* (STL), sfruttando algoritmi di intelligenza artificiale per consolidare spedizioni di clienti diversi su uno stesso veicolo e ottimizzare le rotte in maniera automatica. A differenza delle spedizioni LTL tradizionali, il carico viaggia sullo stesso veicolo lungo l'intero percorso, evitando passaggi intermedi nei centri di smistamento.

Sul versante del monitoraggio, le soluzioni IoT per la *cold chain* come Lynx Fleet [1] operano tipicamente come sistemi B2B, scollegati dalla fase commerciale di prenotazione e pricing, e si limitano per lo più a un monitoraggio

basato su soglie statiche che, pur essendo semplice da implementare, non è in grado di rilevare pattern anomali complessi dell'impianto di refrigerazione.

Il presente lavoro propone **ChillChain**, una piattaforma IoT che integra in un'unica soluzione il matching tra domanda e offerta di spedizioni refrigerate e il monitoraggio intelligente della catena del freddo con rilevazione automatica delle anomalie. L'idea alla base del progetto è consentire ai clienti di visualizzare i viaggi già programmati compatibili con le proprie esigenze di spedizione e scegliere a quale viaggio aggregare la propria spedizione. La rotta del veicolo viene ricalcolata dinamicamente per includere le nuove fermate, mentre un sistema di pricing basato sull'occupazione del mezzo applica un divisore esponenziale che rende il costo per singolo cliente progressivamente più conveniente all'aumentare delle spedizioni condivise, incentivando così un utilizzo più efficiente della capacità di trasporto.

Accanto alla componente di marketplace, la piattaforma integra un sistema di monitoraggio in tempo reale dei parametri operativi dei veicoli refrigerati. I dati telemetrici vengono trasmessi via MQTT e analizzati da un servizio dedicato di rilevazione anomalie. Quest'ultimo impiega un LSTM Autoencoder, addestrato sul comportamento nominale dell'impianto, per calcolare l'errore di ricostruzione di ciascuna finestra temporale di osservazione: quando tale errore supera una soglia appresa in fase di training, il sistema genera una notifica che viene inoltrata al tecnico responsabile attraverso la dashboard della piattaforma.

Dal punto di vista architetturale, ChillChain adotta un'architettura a microservizi composta da un backend Spring Boot che gestisce la logica applicativa e le API REST, un frontend React per l'interfaccia utente, un broker MQTT Mosquitto per la comunicazione in tempo reale, due servizi Python dedicati rispettivamente allo streaming dei dati telemetrici e alla rilevazione delle anomalie, e un database MongoDB per la persistenza. L'intera infrastruttura è orchestrata tramite Docker Compose, garantendo riproducibilità e semplicità di deployment. L'obiettivo del progetto è dimostrare la fattibilità di un approccio integrato che unisca la dimensione commerciale della logistica collaborativa con quella tecnica del monitoraggio.

Capitolo 2

Analisi dei Requisiti

In questo capitolo vengono descritti i requisiti funzionali e non funzionali che il sistema ChillChain è chiamato a soddisfare. L'analisi è stata condotta considerando i tre profili utente previsti dalla piattaforma — amministratore, cliente e tecnico.

2.1 Requisiti Funzionali

I requisiti funzionali definiscono le capacità operative che la piattaforma deve offrire ai propri utenti e descrivono il comportamento atteso del sistema in risposta a specifiche azioni o eventi.

2.1.1 Gestione degli utenti e autenticazione

Il sistema deve consentire la registrazione autonoma dei clienti mediante email e password. L'amministratore deve poter creare nuovi account per i tecnici, assegnando loro le credenziali di accesso. L'autenticazione avviene tramite credenziali protette e, al momento del login, il sistema assegna un token di sessione associato al ruolo dell'utente (amministratore, cliente o tecnico).

2.1.2 Gestione della flotta

L'amministratore deve poter registrare nuovi veicoli nella piattaforma, specificando per ciascuno le dimensioni del vano di carico (larghezza, altezza, lunghezza), la portata massima in peso, il costo per chilometro e l'indicazione sulla presenza o meno dell'impianto di refrigerazione. Il sistema deve consentire la visualizzazione dell'intera flotta e la rimozione dei veicoli non più operativi.

2.1.3 Gestione dei viaggi e delle spedizioni

L'amministratore deve poter visualizzare l'elenco dei viaggi programmati e consultare le spedizioni associate a ciascun viaggio.

2.1.4 Ricerca e prenotazione delle spedizioni

Il cliente autenticato deve poter ricercare i viaggi disponibili inserendo l'indirizzo di partenza, l'indirizzo di arrivo, le caratteristiche del proprio pacco — dimensioni, peso, necessità di refrigerazione — e la data entro cui la consegna deve essere completata. Il sistema deve restituire due categorie di risultati: nuovi viaggi, generati a partire dai veicoli della flotta ancora privi di viaggi assegnati con percorso calcolato ad hoc, e viaggi condivisi, corrispondenti a viaggi già programmati che dispongano di capacità residua sufficiente e di compatibilità geografica con il percorso richiesto. Per i viaggi condivisi, il prezzo deve essere ricalcolato applicando un meccanismo di divisione basato sul numero di spedizioni già presenti, in modo da incentivare la condivisione del veicolo. Il cliente seleziona il viaggio desiderato tra quelli proposti. Alla conferma della selezione, il sistema deve: nel caso di un nuovo viaggio, crearlo automaticamente con il percorso calcolato; nel caso di un viaggio condiviso, ricalcolare dinamicamente il percorso introducendo le fermate del nuovo cliente come tappe intermedie.

2.1.5 Consultazione delle spedizioni del cliente

Il cliente autenticato deve poter consultare l'elenco delle proprie spedizioni, con i relativi dettagli quali indirizzi di partenza e arrivo, dimensioni e peso del pacco, veicolo assegnato e prezzo.

2.1.6 Monitoraggio telemetrico in tempo reale

Il sistema deve acquisire i dati telemetrici provenienti dai sensori installati a bordo dei veicoli refrigerati. Il tecnico deve poter visualizzare i dati telemetrici attraverso una dashboard che presenti l'andamento temporale dei parametri mediante grafici, con la possibilità di filtrare per veicolo, per tipologia di dato telemetrico e per periodo temporale.

2.1.7 Rilevazione delle anomalie

Un servizio dedicato deve analizzare in maniera continuativa i flussi telemetrici provenienti dai veicoli e identificare automaticamente condizioni anomale.

Quando un'anomalia viene confermata, il sistema deve generare una notifica persistente, associata al veicolo interessato.

2.1.8 Gestione delle notifiche

Il tecnico deve poter consultare l'elenco delle notifiche ricevute, ciascuna contenente il nome del veicolo, il timestamp dell'evento, l'errore di ricostruzione e un messaggio descrittivo dell'anomalia rilevata.

2.1.9 Reportistica della flotta

Il tecnico deve poter accedere a una sezione dedicata ai report, che comprende tre tipologie di analisi:

- **Ore operative**: vista mensile, per ciascun veicolo, dei giorni in cui le celle frigorifere sono state in funzione, con possibilità di drill-down giornaliero per analizzare le fasce orarie di funzionamento;
- **Ore cumulative**: distribuzione del numero di ore di funzionamento delle celle frigorifere dei veicoli in un intervallo temporale selezionabile, presentata sotto forma di istogramma;
- **Report anomalie**: conteggio delle anomalie rilevate per veicolo, con granularità configurabile (anno, mese, giorno).

Per ciascun report, il tecnico deve poter esportare i dati in formato CSV.

2.2 Requisiti Non Funzionali

I requisiti non funzionali specificano le qualità architetturali e operative che il sistema deve garantire trasversalmente rispetto alle singole funzionalità.

2.2.1 Usabilità

L'interfaccia utente deve essere progettata con particolare attenzione alla chiarezza e all'immediatezza d'uso. Le informazioni devono essere presentate in modo differenziato in base al ruolo dell'utente.

2.2.2 Sicurezza

Il sistema deve proteggere le comunicazioni tra client e server mediante autenticazione basata su token JWT e assegnazione dei ruoli agli utenti autenticati. Le password degli utenti devono essere memorizzate in forma cifrata. L'accesso alle risorse deve essere regolato in base al ruolo, impedendo a utenti non autorizzati di accedere a funzionalità riservate ad altri profili.

2.2.3 Modularità e manutenibilità

L'architettura del sistema deve seguire il paradigma a microservizi, con una separazione netta tra le componenti applicative. Ogni componente deve poter essere sviluppato, testato e aggiornato indipendentemente dagli altri.

2.2.4 Portabilità e riproducibilità del deployment

L'intera infrastruttura deve essere containerizzata tramite Docker e orchestrata mediante Docker Compose, in modo da garantire che il sistema possa essere avviato in maniera identica su qualsiasi macchina che disponga del runtime Docker.

Capitolo 3

Stato dell'Arte

In questo capitolo vengono analizzate le principali soluzioni nel campo della logistica collaborativa, del monitoraggio IoT della catena del freddo e della rilevazione di anomalie su serie temporali, con una sintesi e un'analisi critica dei loro limiti rispetto alla soluzione proposta.

3.1 Flock Freight – FlockDirect® Shared Truckload

Flock Freight è un'azienda statunitense che ha introdotto il concetto di *Shared Truckload* (STL), una modalità di spedizione che consente di consolidare carichi di clienti diversi su un unico camion mediante una tecnologia brevettata basata su intelligenza artificiale. L'algoritmo di Flock Freight analizza posizioni geografiche, calendari di spedizione e dimensioni dei carichi per individuare, tra miliardi di combinazioni possibili, gli abbinamenti più efficienti, instradando il veicolo su percorsi diretti senza passaggi in magazzini intermedi [2]. A differenza del tradizionale LTL (*Less Than Truckload*), in cui la merce viene scaricata e ricaricata più volte lungo il percorso, nello STL il carico non lascia mai il veicolo fino alla consegna, riducendo drasticamente il rischio di danneggiamento e i tempi di transito.

Il modello di Flock Freight presenta caratteristiche differenti rispetto all'approccio proposto in ChillChain. Dal punto di vista dell'ottimizzazione, Flock adotta un approccio flessibile basato su AI che può combinare spedizioni con origini e destinazioni diverse, individuando configurazioni di trasporto efficienti sull'intera rete logistica. ChillChain segue invece un approccio spazialmente più rigido: le spedizioni condivise devono trovarsi lungo il percorso già programmato del veicolo, con una tolleranza massima di deviazione sia in termini di distanza dalla rotta sia di incremento della durata del viaggio.

Questo vincolo riduce il numero di combinazioni possibili, ma quando il matching avviene, il risparmio è potenzialmente più elevato, poiché la deviazione introdotta è minima e la riduzione di prezzo scala in modo aggressivo con il numero di spedizioni a bordo. Si tratta di due approcci alternativi, ciascuno con i propri compromessi tra flessibilità e ottimizzazione del costo. Inoltre, la piattaforma Flock Freight è progettata per il trasporto merci generico e non integra alcuna funzionalità di monitoraggio della catena del freddo: non offre strumenti di telemetria né di rilevazione anomalie per spedizioni refrigerate.

3.2 Carrier Lynx Fleet – Piattaforma digitale per il monitoraggio della catena del freddo

Carrier Lynx Fleet è una piattaforma di telematica sviluppata da Carrier Transicold, divisione di Carrier Global Corporation, nell'ambito dell'ecosistema Lynx realizzato in collaborazione con Amazon Web Services (AWS) [1]. La piattaforma utilizza tecnologie IoT e analytics per monitorare in tempo reale i sistemi di refrigerazione installati su truck, trailer e container. I sensori raccolgono dati operativi come temperatura, stato dell'unità refrigerante e posizione GPS, che vengono aggregati e visualizzati in una dashboard centralizzata per la gestione delle flotte.

La piattaforma offre funzionalità di monitoraggio remoto, notifiche automatiche e strumenti di diagnostica e manutenzione predittiva, ed è distribuita come soluzione SaaS integrabile con sistemi TMS (Trasportation Management Systems) e WMS (Warehouse Management Systems).

A differenza di ChillChain, Lynx Fleet è una piattaforma di gestione e monitoraggio della flotta e non include componenti di marketplace per il matching tra domanda e offerta di spedizioni. Inoltre, la rilevazione delle anomalie è principalmente basata su regole e soglie operative per la manutenzione dell'equipaggiamento, mentre ChillChain utilizza un modello LSTM Autoencoder per individuare pattern anomali nelle condizioni ambientali del carico.

3.3 Rilevazione anomalie su serie temporali IoT

Tra i contributi più rilevanti, Malhotra et al. [4] propongono un *LSTM-based Encoder-Decoder* per la rilevazione di anomalie su dati multi-sensoriali,

dimostrando come la ricostruzione della sequenza di input tramite LSTM consenta di identificare efficacemente condizioni anomale. Wei et al. [6] applicano un LSTM-Autoencoder a serie temporali sulla qualità dell'aria, evidenziando come la combinazione di ricostruzione e predizione permetta di rilevare pattern anomali sottili in contesti multivariati. Hu et al. [3] mostrano l'applicazione di LSTM Autoencoder per l'anomaly detection su dati industriali di sensori, confermando la bontà di questo approccio per sistemi complessi con più variabili di input.

Questi lavori forniscono le basi teoriche per l'adozione di LSTM Autoencoder nella piattaforma **ChillChain**, dove un encoder LSTM comprime la sequenza di input in uno spazio latente e un decoder LSTM la ricostruisce, generando un errore di ricostruzione utilizzato come indicatore di anomalie.

3.4 Sintesi e posizionamento della soluzione proposta

Dall'analisi dello stato dell'arte emerge che le soluzioni esistenti affrontano separatamente i tre ambiti considerati in questo lavoro: il matching tra domanda e offerta di spedizioni, il monitoraggio IoT della catena del freddo e la rilevazione di anomalie tramite deep learning. Flock Freight offre meccanismi di consolidamento dei carichi, ma non integra funzionalità per il monitoraggio di spedizioni refrigerate. Carrier Lynx Fleet fornisce strumenti avanzati di telemetria e gestione delle flotte refrigerate, ma non include componenti di marketplace né sistemi di anomaly detection basati su LSTM Autoencoder.

L'approccio basato su LSTM Autoencoder, evidenziato da Malhotra et al. [4], Wei et al. [6] e Hu et al. [3], rappresenta una delle tecniche più promettenti per l'anomaly detection su serie temporali multivariate, permettendo di rilevare deviazioni sottili e pattern complessi nei dati IoT.

ChillChain colma questo gap proponendo una piattaforma integrata che combina un marketplace con pricing dinamico basato sull'occupazione del veicolo, un sistema di monitoraggio IoT in tempo reale e un servizio di rilevazione anomalie basato su LSTM Autoencoder. In questo modo, la piattaforma non solo facilita la logistica collaborativa per spedizioni refrigerate, ma consente anche di individuare tempestivamente potenziali malfunzionamenti dei veicoli, offrendo una soluzione completa sia per la dimensione commerciale sia per quella tecnica della supply chain.

Capitolo 4

Tecnologie Utilizzate

In questo capitolo vengono descritte le principali tecnologie impiegate nella realizzazione di ChillChain, evidenziando come ciascuna abbia contribuito alla soluzione complessiva.

4.1 Spring Boot

Spring Boot è il framework Java scelto per lo sviluppo del backend della piattaforma, per la sua capacità di semplificare la configurazione e la gestione di applicazioni complesse.

Nel contesto di ChillChain, Spring Boot gestisce le API REST che coordinano il ciclo di vita delle entità di dominio: veicoli, viaggi, spedizioni, notifiche e utenti. Spring Security implementa l'autenticazione tramite token JWT. L'integrazione con MongoDB avviene tramite Spring Data MongoDB, che consente l'utilizzo di repository dichiarativi e pipeline di aggregazione personalizzate. Un elemento chiave è l'integrazione con il protocollo MQTT tramite Spring Integration: il backend sottoscrive i topic di telemetria e anomalie pubblicati dai servizi Python, riceve i messaggi tramite channel adapter e li instrada ai service activator responsabili della persistenza dei dati e della generazione delle notifiche.

4.2 React e TypeScript

Il frontend di ChillChain è una SPA (Single Page Application), realizzato con React, una libreria JavaScript basata su componenti, combinata con TypeScript, un superset tipizzato di JavaScript che aggiunge controllo statico dei tipi.

React ha permesso di strutturare l'interfaccia come un insieme di componenti riutilizzabili, ciascuno responsabile di una porzione specifica della vista. La gestione dello stato applicativo si affida agli hook nativi (`useState`, `useEffect`) e a `localStorage` per la persistenza delle informazioni di sessione. La visualizzazione dei dati telemetrici in tempo reale utilizza la libreria Recharts, mentre le tratte dei veicoli vengono mostrate su mappa interattiva tramite React-Leaflet. Il progetto frontend è costruito con Vite e stilizzato con Tailwind CSS, garantendo un'interfaccia coerente e responsive.

4.3 MQTT e Mosquitto

MQTT (*Message Queuing Telemetry Transport*) è il protocollo leggero basato sul pattern *publish/subscribe* adottato per lo scambio dei dati telemetrici tra i servizi della piattaforma.

In ChillChain, MQTT connette tre attori principali: il servizio di streaming dei dati (publisher), il servizio di anomaly detection (subscriber e publisher) e il backend Spring Boot (subscriber). Il broker Mosquitto gestisce l'instradamento dei messaggi tramite topic.

4.4 MongoDB

MongoDB è il database NoSQL orientato ai documenti impiegato per la persistenza di tutti i dati della piattaforma.

Nel contesto di ChillChain, la flessibilità di MongoDB si è rivelata particolarmente vantaggiosa per la gestione dei dati telemetrici, la cui struttura può variare in funzione del tipo di sensore, e per le entità di dominio come viaggi e spedizioni, che includono campi con struttura annidata (coordinate geografiche, polyline). L'interazione avviene tramite Spring Data MongoDB, che mappa automaticamente le classi Java alle collezioni corrispondenti. Un aspetto specifico del progetto è l'uso delle pipeline di aggregazione di MongoDB per implementare la logica di ricerca dei viaggi già programmati.

4.5 Python, FastAPI e PyTorch

Python è il linguaggio utilizzato per i due microservizi dedicati rispettivamente allo streaming dei dati telemetrici e alla rilevazione delle anomalie. La scelta è motivata dalla ricchezza dell'ecosistema Python per il *data processing* e il *machine learning*.

Il servizio di streaming (`streamer_main.py`) è un'applicazione FastAPI che legge i file CSV contenenti i dati simulati di telemetria e li pubblica sul broker MQTT con una cadenza configurabile, simulando il comportamento di sensori reali installati a bordo dei veicoli. I dataset sono generati da uno script di simulazione termodinamica (`stream_fridge_dataset_generator.py`), derivato dal dataset Kaggle *Simulated Refrigerator Fault Diagnosis* [5], che modella il comportamento fisico di un impianto frigorifero.

Il servizio di anomaly detection (`anomaly_main.py`) è anch'esso un'applicazione FastAPI che sottoscrive il topic telemetria via MQTT, analizza i dati in ingresso e pubblica i risultati sul topic anomalie. Il cuore del servizio è un modello LSTM Autoencoder implementato in PyTorch: l'encoder, una rete LSTM, comprime la sequenza temporale di ingresso in una rappresentazione latente a dimensionalità ridotta; il decoder, un'altra rete LSTM, ricostruisce la sequenza originale a partire da tale rappresentazione. L'errore di ricostruzione, calcolato come errore quadratico medio (MSE) tra input e output, viene confrontato con una soglia appresa durante l'addestramento su dati di funzionamento normale. Lo scaler, serializzato con Pickle, normalizza le quindici feature in ingresso per garantire che parametri con scale numeriche molto diverse contribuiscano in modo equilibrato all'errore di ricostruzione. La libreria Pandas è impiegata per la lettura dei CSV e la preparazione dei DataFrame, mentre NumPy gestisce le operazioni numeriche sui buffer a finestra scorrevole.

4.6 Google Maps Platform

Le API di Google Maps Platform sono utilizzate per il calcolo dei percorsi, la geolocalizzazione degli indirizzi e l'assistenza all'inserimento degli stessi da parte degli utenti. Il sistema impiega tre servizi distinti, distribuiti tra frontend e backend.

Sul lato frontend, il componente di inserimento spedizione integra la *Places Autocomplete API*, che fornisce suggerimenti in tempo reale durante la digitazione degli indirizzi di ritiro e consegna. Oltre a migliorare l'esperienza utente riducendo errori di battitura e ambiguità, il servizio restituisce direttamente le coordinate geografiche associate all'indirizzo selezionato, eliminando la necessità di una successiva chiamata di geocodifica.

Sul lato backend vengono utilizzate due API aggiuntive: la *Geocoding API*, che converte gli indirizzi testuali in coordinate geografiche (latitudine e longitudine) nei casi in cui le coordinate non siano già disponibili dal frontend, e la *Routes API*, che calcola il percorso ottimale tra due o più punti

restituendo la distanza in metri, la durata stimata e la polyline codificata del tracciato.

4.7 Docker e Docker Compose

Docker è la piattaforma di containerizzazione impiegata per isolare ciascun componente dell'architettura in un ambiente di esecuzione autonomo e riproducibile. Ogni servizio della piattaforma viene eseguito all'interno di un container dedicato, con le proprie dipendenze e la propria configurazione.

Docker Compose orchestra l'avvio coordinato di tutti i container, definendo in un unico file YAML le immagini, le porte esposte, le variabili d'ambiente, i volumi persistenti e le reti interne.

Capitolo 5

Soluzione Proposta

In questo capitolo viene descritta in dettaglio la soluzione realizzata, partendo dall'architettura complessiva del sistema per poi approfondire il funzionamento logico di ciascun componente e i principali dettagli implementativi. La piattaforma ChillChain si compone di tre macro-funzionalità integrate: un sistema di gestione della flotta e dei viaggi riservato all'amministratore, un marketplace per il trasporto condiviso refrigerato e non, e un sistema di monitoraggio in tempo reale con rilevazione automatica delle anomalie.

5.1 Architettura del sistema

L'architettura di ChillChain segue il paradigma a microservizi, in cui ciascun componente è responsabile di una funzione specifica e comunica con gli altri attraverso interfacce ben definite. La Figura 5.1 illustra schematicamente i servizi e i flussi di comunicazione.

Il sistema è composto da sei servizi containerizzati, orchestrati tramite Docker Compose:

Il **backend Spring Boot** (porta 8081) rappresenta il nucleo applicativo: espone le API REST per la gestione di veicoli, viaggi, spedizioni, utenti e notifiche, implementa l'autenticazione JWT e la logica di autorizzazione basata sui ruoli, sottoscrive i topic MQTT per ricevere telemetria e risultati dell'anomaly detection, e persiste tutti i dati su MongoDB.

Il **frontend React** (porta 5173) fornisce l'interfaccia utente, differenziata per ruolo.

Il **broker MQTT Mosquitto** (porta 1883) gestisce la comunicazione asincrona tra i servizi Python e il backend, instradando i messaggi attraverso topic.

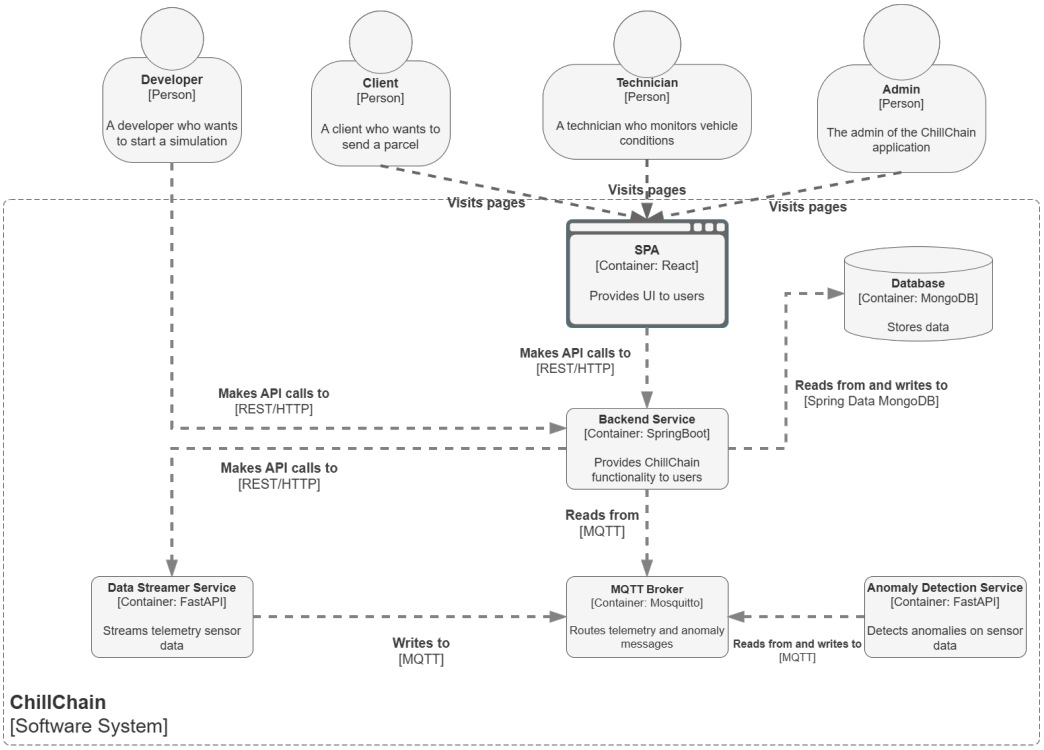

Figura 5.1: Architettura a microservizi di ChillChain.

Il **servizio di streaming** (porta 8002) simula i sensori a bordo dei veicoli, leggendo dataset CSV e pubblicando i dati telemetrici sul broker MQTT con una cadenza di un messaggio al secondo.

Il **servizio di anomaly detection** (porta 8003) sottoscrive la telemetria pubblicata dallo streamer, la analizza con il modello LSTM Autoencoder e pubblica i risultati su un topic dedicato.

Infine, **MongoDB** (porta 27017) funge da database centralizzato, organizzato in sei collezioni: `user`, `vehicle`, `trip`, `shipment`, `telemetry` e `notification`.

5.2 Gestione degli utenti e autenticazione

Il sistema prevede tre ruoli distinti, ciascuno con un perimetro di azioni e una vista dell'interfaccia dedicati:

- **ADMIN**: crea nuovi account per i tecnici, gestisce la flotta (aggiunta e rimozione di veicoli), visualizza l'elenco dei viaggi programmati e le spedizioni associate.

- **CLIENT**: si registra autonomamente sulla piattaforma, ricerca viaggi compatibili con le proprie esigenze di spedizione, confronta le opzioni disponibili (inizializzazione di un nuovo viaggio o condivisione di un viaggio già esistente con altre spedizioni), prenota la spedizione e consulta lo storico delle proprie spedizioni.
- **TECHNICIAN**: accede alla dashboard di monitoraggio, visualizza lo storico telemetrico dei veicoli, gestisce le notifiche di anomalia e consulta i report sulla flotta.

La registrazione del cliente avviene tramite un form pubblico che richiede email e password; il backend forza il ruolo a `CLIENT` lato server, impedendo l'auto-assegnazione di ruoli privilegiati. La creazione dei tecnici è invece riservata all'amministratore, che accede a una schermata dedicata per inserire le credenziali del nuovo tecnico con ruolo `TECHNICIAN` preassegnato.

L'autenticazione è implementata tramite token JWT (*JSON Web Token*). All'atto del login, il backend verifica le credenziali — la password è memorizzata con hashing Argon2 — e genera un token firmato contenente l'email dell'utente e il suo ruolo. Il token viene incluso nell'header `Authorization` di ogni richiesta successiva e validato da un filtro che precede l'elaborazione della richiesta stessa. La catena di sicurezza Spring Security definisce quali endpoint sono accessibili a ciascun ruolo: ad esempio, le operazioni di gestione della flotta richiedono il ruolo `ADMIN`, la ricerca e prenotazione dei viaggi e la consultazione delle proprie spedizioni richiedono il ruolo `CLIENT`, mentre l'accesso alla telemetria, alle notifiche e ai report è riservato al ruolo `TECHNICIAN`. Gli endpoint di autenticazione e di registrazione del cliente sono invece pubblici.

5.3 Gestione della flotta e dei viaggi

L'amministratore dispone di tre schermate dedicate alla gestione operativa della piattaforma: la registrazione di nuovi veicoli, la consultazione della flotta e il monitoraggio dei viaggi programmati.

5.3.1 Aggiunta di un veicolo

Il form di registrazione raccoglie i dati caratteristici del veicolo: nome identificativo, dimensioni del vano di carico (lunghezza, larghezza e altezza in centimetri), portata massima in chilogrammi, presenza di un impianto di refrigerazione e costo chilometrico in euro. Il frontend esegue una validazione preliminare che impedisce l'invio del form se uno qualsiasi dei campi risulta

vuoto o non valido. Al completamento, il backend verifica l'unicità del nome e persiste il documento nella collezione `vehicle` di MongoDB. In caso di successo, l'interfaccia mostra un modale di conferma e azzera tutti i campi, consentendo l'immediata registrazione di un ulteriore mezzo.

5.3.2 Lista veicoli

La schermata di gestione della flotta elenca tutti i veicoli registrati in forma tabellare, esponendo per ciascuno le dimensioni, la portata, il prezzo per chilometro e la presenza della refrigerazione. Per ogni veicolo è disponibile un'azione di eliminazione: prima di procedere, l'interfaccia richiede una conferma esplicita tramite un modale dedicato. Lato backend, l'operazione è implementata come cancellazione a cascata: vengono rimossi, nell'ordine, tutti gli shipment associati al veicolo, il trip corrispondente e infine il documento veicolo stesso, garantendo la coerenza referenziale dei dati.

5.3.3 Lista viaggi

La schermata dei viaggi presenta tutti i viaggi in programma con le informazioni principali: veicolo assegnato, data di arrivo prevista, distanza totale del percorso e capacità residua. Ciascuna riga è espandibile: selezionando un viaggio, il sistema recupera dal backend la lista degli shipment associati e li mostra in una sotto-tabella con indirizzo di partenza, indirizzo di arrivo, dimensioni del pacco e prezzo. Da questa vista l'amministratore può eliminare l'intero trip con tutti gli shipment collegati.

Per ogni viaggio è inoltre disponibile un'anteprima cartografica: un popup mostra il percorso complessivo decodificato dalla polyline del viaggio su Google Maps. Analogamente, ciascuno shipment espone una propria anteprima cartografica che evidenzia il tratto specifico della spedizione, con marcatori distinti per il punto di ritiro e quello di consegna.

5.4 Marketplace: ricerca dei viaggi disponibili e creazione della spedizione

Il cuore della piattaforma è il meccanismo che consente ai clienti di creare spedizioni.

5.4.1 Fase 1 — Ricerca dei veicoli disponibili per un nuovo viaggio

Quando un cliente inserisce i dati della propria spedizione (indirizzo di partenza e arrivo, dimensioni, peso, necessità di refrigerazione e data di arrivo desiderata), il backend esegue una prima query per individuare i veicoli della flotta che soddisfano i requisiti e che non hanno ancora alcun viaggio assegnato. Questa query è implementata come aggregation pipeline su MongoDB in tre stadi: il primo filtra i veicoli verificando che ciascuna dimensione del vano (larghezza, altezza, lunghezza) sia sufficiente a contenere il pacco e che il peso massimo e la tipologia di refrigerazione siano compatibili; il secondo esegue un `$lookup` sulla collezione `trip`; il terzo seleziona solo i veicoli il cui array di viaggi risulta vuoto. Il sistema invoca quindi la Routes API di Google Maps per calcolare il percorso tra la partenza e l'arrivo indicati dal cliente, ottenendo distanza, durata e polyline codificata. Questo percorso viene associato a ciascun veicolo disponibile, il cui prezzo è determinato come prezzo = distanceKm × pricePerKm.

5.4.2 Fase 2 — Ricerca dei viaggi già programmati

Parallelamente, il sistema cerca viaggi già programmati che abbiano capacità residua sufficiente e data di arrivo compatibile. Anche questa ricerca è implementata come aggregation pipeline: il primo stadio esegue un `$lookup` con la collezione `vehicle` per recuperare la tipologia di refrigerazione; il secondo filtra per capacità residua, refrigerazione e data.

5.4.3 Fase 3 — Validazione geografica dei viaggi già programmati

I viaggi già programmati individuati nella fase precedente vengono ulteriormente filtrati verificando la compatibilità geografica con la spedizione richiesta. Per ciascun viaggio candidato, il sistema decodifica la polyline del percorso e calcola la distanza geodetica (formula di Haversine) tra i punti di ritiro e consegna del nuovo pacco e il tracciato del viaggio. Se entrambi i punti distano meno di 1,5 km dalla polyline, la tratta è considerata geograficamente compatibile. Un ulteriore controllo verifica che il punto di ritiro preceda quello di consegna lungo il percorso, impedendo deviazioni illogiche.

5.4.4 Fase 4 — Ricalcolo del percorso con waypoint

Per le tratte che superano la validazione geografica, il sistema ricalcola il percorso includendo i waypoint intermedi di tutti gli shipment (sia quelli già assegnati sia quello nuovo). L'ordinamento dei waypoint è affidato a un algoritmo greedy con vincoli: partendo dalla posizione corrente, seleziona il waypoint disponibile più vicino, rispettando il vincolo che il punto di ritiro di ciascuna spedizione debba essere visitato prima del corrispondente punto di consegna. Un delivery diventa "disponibile" solo dopo che il relativo pickup è stato inserito nella sequenza. Il percorso ricalcolato viene confrontato con quello originale: se la differenza di durata non supera i 30 minuti, la tratta viene inclusa tra i risultati.

5.4.5 Fase 5 — Pricing con divisore esponenziale

Il sistema di pricing incentiva la condivisione attraverso un divisore esponenziale. Se il veicolo ospita già n spedizioni, il prezzo per il nuovo cliente viene calcolato come:

$$\text{prezzo} = \frac{\text{distanceKm}_{\text{shipment}} \times \text{pricePerKm}_{\text{vehicle}}}{2^n} \tag{1}$$

Dove $\text{distanceKm}_{\text{shipment}}$ è la distanza del tratto specifico del nuovo cliente e n è il numero di spedizioni già presenti. In questo modo, la prima spedizione paga il prezzo pieno, la seconda paga metà, la terza un quarto e così via. Questo meccanismo crea un incentivo economico crescente: più il veicolo è occupato, più il trasporto diventa conveniente per i nuovi clienti, incentivando il riempimento del mezzo e riducendo i costi per tutti i partecipanti.

5.4.6 Selezione e conferma della tratta

Il cliente visualizza tutte le opzioni — viaggi nuovi e viaggi già esistenti. Dopo la selezione del viaggio, il backend esegue l'operazione seguente: se il viaggio è nuovo (veicolo senza trip assegnato), viene creata una nuova entità `Trip`; se il viaggio è già esistente, viene aggiornata l'entità `Trip` esistente con il nuovo percorso (inclusivo dei waypoint) e la capacità residua aggiornata. In entrambi i casi, viene creata un'entità `Shipment` associato al viaggio.

5.5 Consultazione delle spedizioni del cliente

Il cliente autenticato può accedere alla pagina delle proprie spedizioni, che elenca tutte le spedizioni associate al suo account. L'identificativo del cliente

viene estratto lato server dal token JWT, garantendo che ciascun utente possa visualizzare esclusivamente le proprie spedizioni senza possibilità di accesso a quelle altrui. Per ciascuna spedizione vengono mostrati: indirizzo di partenza e arrivo, dimensioni e peso del pacco, veicolo assegnato, prezzo e data di arrivo prevista.

5.6 Generazione dei dati telemetrici

La simulazione della telemetria di bordo si basa su un modello termodinamico che riproduce il comportamento fisico di un impianto frigorifero a compressione di vapore. Il generatore, derivato dal dataset Kaggle *Simulated Refrigerator Fault Diagnosis* [5], produce dataset CSV contenenti 120 campioni da 15 feature ciascuno (un campione rappresenta dati estratti in un certo minuto), strutturati in due fasi: i primi 60 minuti in condizioni normali, seguiti da 60 minuti con un guasto iniettato. Sono previste varie tipologie di guasto, tra cui: fouling del condensatore (lieve e severo), degradazione e guasto della ventola dell'evaporatore, ecc.

Il servizio di streaming legge questi CSV e pubblica ciascuna riga sul topic MQTT `fridge/{vehicleName}/telemetry` con un intervallo configurabile (default: 1 secondo), includendo un timestamp ISO e un indice di riga progressivo. Al termine del dataset, pubblica un messaggio di completamento con `stream_status: "completed"`, che segnala agli altri servizi la fine dello stream.

5.7 Pipeline di anomaly detection

La rilevazione delle anomalie si articola in tre fasi: l'addestramento offline del modello, l'inferenza in tempo reale e il meccanismo di smoothing per la riduzione dei falsi positivi.

5.7.1 Addestramento del modello

Il modello LSTM Autoencoder è stato addestrato su Google Colab con GPU Tesla T4, utilizzando un dataset composto esclusivamente da dati di funzionamento normale. L'architettura del modello è la seguente: un encoder LSTM con 15 feature in ingresso e hidden size pari a 16, uno strato lineare di compressione che riduce la rappresentazione a uno spazio latente di dimensione 8, due strati lineari che inizializzano hidden state e cell state del decoder a partire dalla rappresentazione latente, un decoder LSTM con hidden size 16 alimentato da una sequenza di zeri (la ricostruzione dipende interamente

dallo stato latente) e uno strato lineare di output che proietta la dimensione nascosta nelle 15 feature originali.

La soglia di anomalia è stata determinata calcolando l'MSE di ricostruzione su tutto il dataset di training normale e prendendo il 95° percentile della distribuzione risultante (threshold $= 0,009868$).

5.7.2 Inferenza in tempo reale

Il servizio di anomaly detection sottoscrive il topic `fridge/+/telemetry` tramite il broker MQTT, ricevendo i dati di tutti i veicoli. Per ciascun veicolo viene creato dinamicamente un'istanza di `VehicleAnomalyDetector` alla ricezione del primo messaggio, garantendo il supporto simultaneo di più veicoli con buffer e contatori indipendenti.

Ad ogni messaggio ricevuto, le 15 feature vengono estratte, normalizzate con lo scaler e inserite in un buffer a finestra scorrevole di 30 campioni. Quando il buffer è pieno, la finestra viene convertita in un tensore PyTorch e passata al modello in modalità di inferenza (`torch.no_grad()`). L'errore di ricostruzione, calcolato come MSE tra input e output mediato su tutti i timestep e tutte le feature, viene confrontato con la soglia. Al completamento dello stream, il detector del veicolo viene rimosso e le sue risorse liberate.

5.7.3 Smoothing con contatori consecutivi

Per evitare che oscillazioni transitorie dell'errore di ricostruzione generino falsi allarmi, il sistema implementa un meccanismo di smoothing basato su contatori consecutivi. Vengono mantenuti due contatori per ciascun veicolo: un `anomaly_counter`, che si incrementa ad ogni campione con MSE $>$ threshold e si azzera al primo campione normale, e un `normal_counter`, che opera in modo simmetrico. La transizione dallo stato normale allo stato di anomalia avviene solo quando il contatore di anomalie supera la soglia di 20 campioni consecutivi; analogamente, il ritorno allo stato normale richiede 20 campioni consecutivi sotto soglia. Questo meccanismo introduce un ritardo controllato nella segnalazione (20 minuti con campionamento al minuto), ma elimina le notifiche spurie causate da picchi isolati, come quelli associati alle aperture della porta o ai cicli di sbrinamento.

Il risultato dell'analisi viene pubblicato sul topic `fridge/{vehicleName}/anomalies`, includendo l'errore di ricostruzione, lo stato dei contatori e, nelle sole transizioni di stato, un messaggio di allerta che il backend persisterà come notifica.

5.8 Gestione delle notifiche

Il backend sottoscrive il topic `fridge/+/anomalies` tramite un channel adapter Spring Integration dedicato. Alla ricezione di un messaggio di anomalia, il backend verifica la presenza del campo `alertMessage`: se presente, indica una transizione di stato (da normale ad anomalia) e genera una nuova notifica persistente su MongoDB con i campi: nome del veicolo, timestamp, errore di ricostruzione, indice di riga e messaggio di allerta. L'interfaccia del tecnico presenta le notifiche in ordine cronologico con un badge numerico che indica il conteggio delle notifiche non lette. Ciascuna notifica può essere contrassegnata come letta tramite un'azione dedicata, aggiornando lo stato sul database.

5.9 Dashboard telemetrica e reportistica

La dashboard di monitoraggio consente al tecnico di visualizzare lo storico telemetrico dei veicoli tramite grafici temporali interattivi. L'interfaccia è organizzata in due livelli: un selettore del veicolo, che elenca i veicoli con refrigerazione, e un pannello di visualizzazione con grafici ad area realizzati tramite Recharts.

Per ciascun veicolo selezionato, il frontend richiede al backend l'elenco completo dei dati telemetrici memorizzati, ordinati cronologicamente. Il tecnico può filtrare la visualizzazione per categoria di parametro (ad esempio, temperature o pressioni) e per intervallo temporale.

5.9.1 Reportistica della flotta

Il tecnico accede a una sezione dedicata ai report, che offre tre tipologie di analisi basate su aggregation pipeline MongoDB eseguite sulla collezione `telemetry` (per i report operativi) e sulla collezione `notification` (per il report anomalie).

Il **report ore operative** presenta una vista mensile in formato heatmap, dove ciascuna cella rappresenta un giorno del mese e la colorazione indica la presenza di attività telemetrica per quel veicolo. L'aggregazione raggruppa i documenti telemetrici per veicolo e giorno, restituendo per ciascun mezzo l'elenco dei giorni attivi nel mese selezionato. Il tecnico può effettuare un drill-down su un singolo giorno per visualizzare le fasce orarie di funzionamento, ottenute mediante un'ulteriore aggregazione che raggruppa per veicolo e ora.

Il **report ore cumulative** mostra la distribuzione del numero di ore di funzionamento delle celle frigorifere dei veicoli in un intervallo temporale selezionabile. L'aggregazione conta le ore distinte (combinazione giorno-ora) con dati telemetrici per ciascun veicolo. Il frontend presenta i risultati sotto forma di istogramma con un numero configurabile di classi e una curva cumulativa percentuale sovrapposta.

Il **report anomalie** conteggia le notifiche di anomalia per veicolo, con granularità progressiva configurabile: anno, mese o giorno. L'aggregazione opera sulla collezione `notification`, filtrando per prefisso temporale e raggruppando per veicolo con ordinamento decrescente per numero di anomalie. Il tecnico può inoltre filtrare per singolo veicolo per un'analisi mirata.

Per ciascun report è disponibile una funzione di esportazione in formato CSV, che consente al tecnico di scaricare i dati per analisi esterne.

Capitolo 6

Validazione Funzionale

In questo capitolo viene descritta la validazione funzionale della piattaforma ChillChain attraverso uno scenario d'uso completo che attraversa tutte le funzionalità del sistema, coinvolgendo i tre ruoli previsti: amministratore, cliente e tecnico. Lo scenario simula un caso realistico in cui un'azienda di trasporti refrigerati gestisce una flotta di veicoli, riceve richieste di spedizione da più clienti e rileva un'anomalia sull'impianto frigorifero durante il viaggio.

6.1 Ambiente di test

La validazione è stata condotta su una macchina locale con l'intero sistema eseguito in container Docker. Il frontend è raggiungibile all'indirizzo `http://localhost:5173`.

Per la simulazione della telemetria è stato predisposto un dataset CSV generato da un script derivato dal codice di simulazione termodinamica descritto nella Sezione 5.6. Il dataset è composto da 1440 righe con campionamento al minuto con iniezione del guasto `UNDERCHARGE_AND_COND_FOUL` (sottocaricamento del refrigerante combinato a fouling del condensatore) a partire dal minuto 900.

6.2 Scenario di validazione

Lo scenario è strutturato in sette fasi che coprono l'intero ciclo di vita di una spedizione, dalla configurazione della flotta fino alla rilevazione di un'anomalia in corso di viaggio e alla consultazione dei report.

6.2.1 Fase 1 — Configurazione della flotta e creazione del tecnico (Amministratore)

L'amministratore accede alla piattaforma con le proprie credenziali tramite il login form mostrato in Figura 6.1.

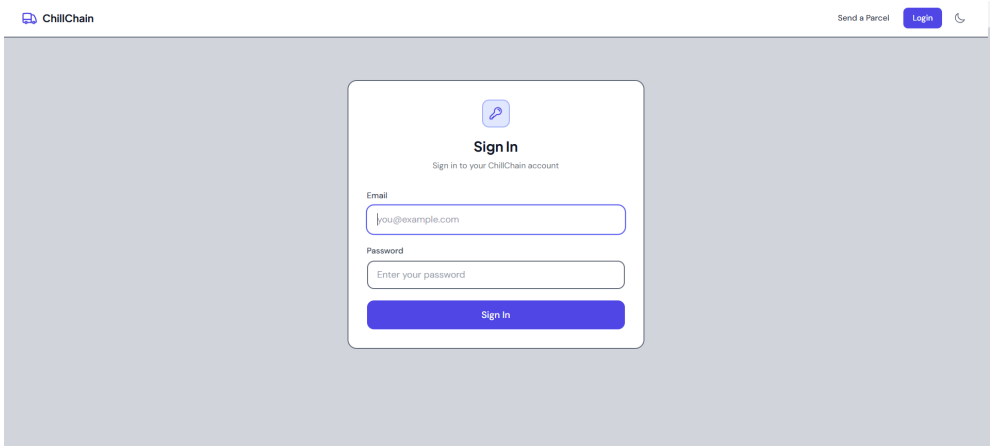

Figura 6.1: Schermata di login della piattaforma. L'utente inserisce email e password; il sistema restituisce un token JWT e fa accedere all'interfaccia corrispondente al ruolo.

Come primo passo, l'amministratore accede alla sezione *Add Technician* (Figura 6.2) per creare l'account del tecnico che si occuperà del monitoraggio della flotta. Il form richiede email e password; il ruolo `TECHNICIAN` viene assegnato automaticamente dal sistema.

Procede, poi, dalla sezione *Add Vehicle* alla registrazione di tre veicoli dalla schermata di registrazione veicoli (Figura 6.3).

Il primo veicolo, denominato `camion1`, è configurato con un vano di carico di $4 \times 2 \times 2$ m, peso massimo 1000 kg, refrigerazione attiva e costo di 1 €/km. Il secondo veicolo, `camion2`, ha dimensioni $3 \times 1.5 \times 1.5$ m, peso massimo 700 kg e un costo di 0,40 €/km, non dispone di refrigerazione. Il terzo veicolo, `camion3`, ha dimensioni $5 \times 2 \times 2$ m, peso massimo 1200 kg e un costo di 1 €/km, dispone di refrigerazione. Nella sezione *Vehicles* (Figura 6.4) è possibile visualizzare la lista dei veicoli registrati, con le relative caratteristiche.

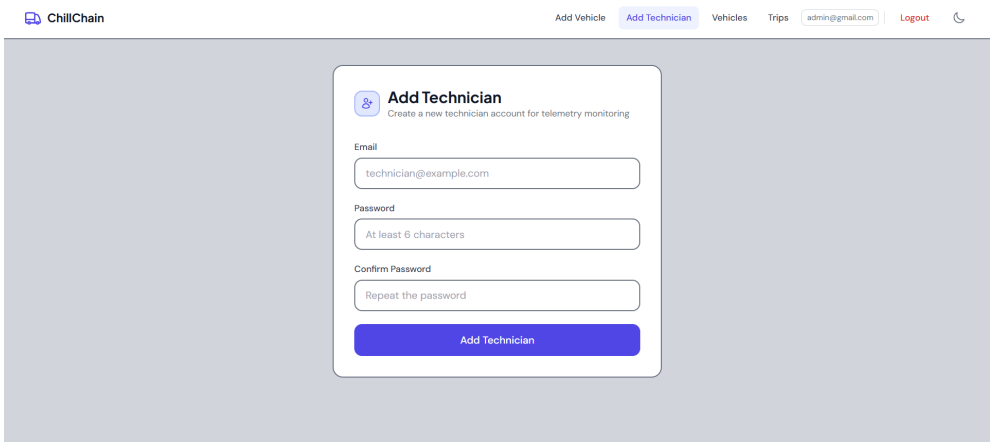

Figura 6.2: Form di creazione di un nuovo tecnico. L'amministratore inserisce email e password; il ruolo `TECHNICIAN` viene assegnato automaticamente dal sistema.

6.2.2 Fase 2 — Registrazione e prima spedizione (Cliente A)

Il Cliente A accede alla piattaforma come utente non autenticato e seleziona *Register* dalla barra di navigazione (Figura 6.5). Compila il form di registrazione con email e password; il backend assegna automaticamente il ruolo `CLIENT` e salva l'account.

Dopo la registrazione, il Cliente A effettua il login e viene indirizzato all'interfaccia dedicata al ruolo cliente.

Dalla sezione *Send Parcel* (Figura 6.6) inserisce i dati della propria spedizione: partenza da Milano, arrivo a Roma, pacco di $50 \times 50 \times 50$ cm con peso di 100 kg, refrigerazione necessaria e data di arrivo entro il 31 marzo 2026.

Il sistema restituisce la lista delle tratte disponibili (Figura 6.7). In questo caso, poiché nessun veicolo ha ancora una tratta assegnata, vengono mostrati entrambi i veicoli come opzioni "vuote": per entrambi 587,89 € (calcolati come distanza Milano–Roma $\times$ prezzo/km del rispettivo veicolo).

Il Cliente A seleziona `camion3`. Il backend crea una nuova entità `Trip` con il percorso Milano–Roma, decrementa la capacità residua del veicolo e salva lo `Shipment` associato.

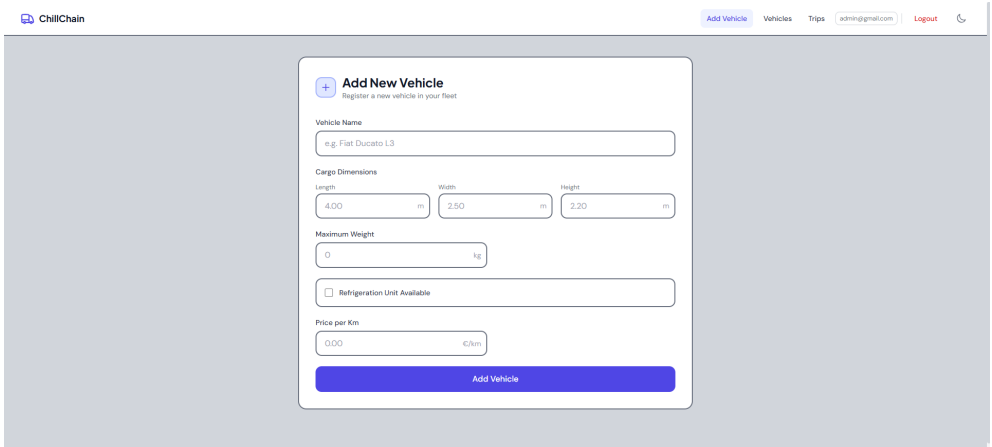

Figura 6.3: Form di registrazione di un nuovo veicolo. L'amministratore specifica il nome identificativo, le dimensioni del vano di carico (lunghezza, larghezza, altezza in m), il peso massimo trasportabile (kg), se è disponibile la refrigerazione e il costo per chilometro (€/km).

6.2.3 Fase 3 — Seconda spedizione: condivisione della tratta (Cliente B)

Un secondo cliente, dopo essersi registrato e autenticato con le stesse modalità del Cliente A, effettua una ricerca per una spedizione da Modena a Firenze, con un pacco più piccolo ($30 \times 30 \times 30$ cm, 20 kg, refrigerato, arrivo massimo il 6 aprile 2026).

Il sistema mostra due opzioni (Figura 6.8): `camion1` per un viaggio nuovo (Modena–Firenze a 142,03 €), `camion3` per un viaggio condiviso (il percorso ricalcolato Milano–Modena–Firenze–Roma rientra nella tolleranza di 1 ora, il prezzo è scontato grazie al divisore 2^1). Il Cliente B seleziona il viaggio in condivisione. Il backend aggiorna la polyline del trip con i nuovi waypoint (Modena e Firenze come tappe intermedie), decrementa ulteriormente la capacità residua e salva il nuovo `Shipment`.

6.2.4 Fase 4 — Consultazione delle spedizioni (Clienti A e B)

Dopo aver completato la prenotazione, ciascun cliente può accedere alla sezione *My Shipments* (Figura 6.9) per verificare le proprie spedizioni. La pagina elenca le spedizioni associate all'account autenticato, con i dettagli di indirizzi di partenza e arrivo, dimensioni e peso del pacco, veicolo assegnato e

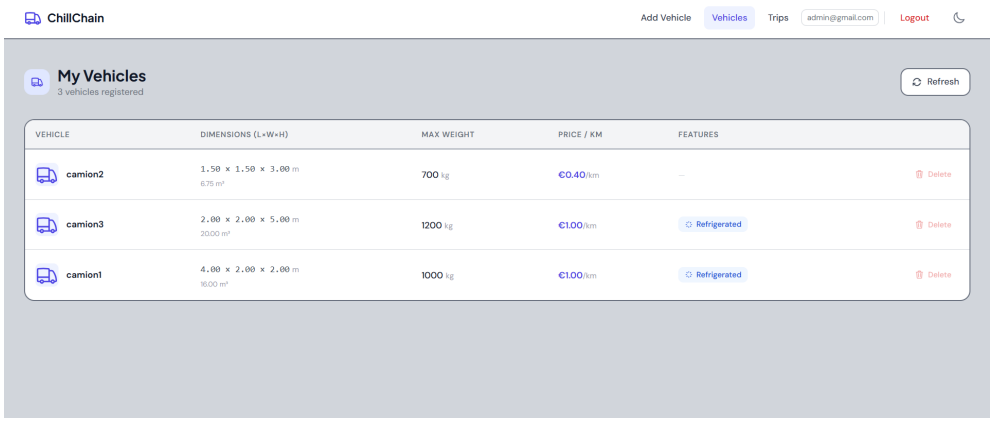

Figura 6.4: Lista dei veicoli registrati nella flotta. Per ciascun veicolo sono visualizzati il nome, le dimensioni, il peso massimo, se è refrigerato e il prezzo per chilometro.

prezzo. L'identificativo del cliente viene estratto dal token JWT lato server, garantendo che ciascun utente visualizzi esclusivamente le proprie spedizioni.

6.2.5 Fase 5 — Visualizzazione dei viaggi programmati e avvio simulazione

L'amministratore può vedere l'elenco dei viaggi programmati dalla sezione *Trips* (Figura 6.10). Per ogni viaggio è possibile visualizzare il percorso in mappa e gli shipment relativi.

Da postman è possibile usare un endpoint del backend per avviare la simulazione della telemetria per `camion3`. Il backend inoltra la richiesta al servizio di streaming, che inizia a pubblicare i dati sul topic `fridge/camion3/telemetry`.

6.2.6 Fase 6 — Rilevazione anomalia e notifica (Tecnico)

Il tecnico accede alla piattaforma con le credenziali create dall'amministratore nella Fase 1 e viene indirizzato alla sezione *Monitor* dove si trova l'elenco dei veicoli dotati di refrigerazione (Figura 6.11).

Durante i primi 900 minuti simulati, il modello LSTM Autoencoder ricostruisce correttamente le sequenze. A partire dal minuto 900 il dataset è influenzato dal guasto `UNDERCHARGE_AND_COND_FOUL`. L'autoencoder inizia a produrre errori di ricostruzione superiori alla soglia. Dopo 20 campioni

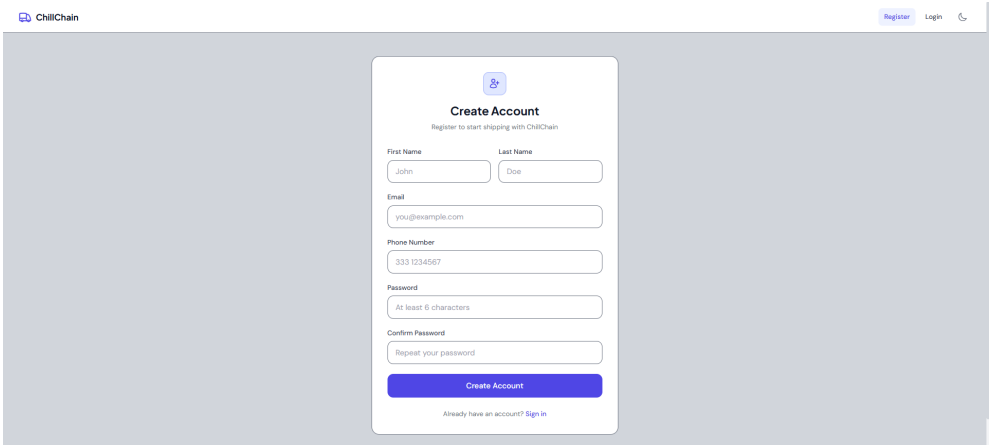

Figura 6.5: Form di registrazione del cliente. L'utente inserisce email e password; il ruolo `CLIENT` viene assegnato automaticamente dal backend.

consecutivi anomali, il servizio di anomaly detection pubblica un messaggio di allerta sul topic `fridge/camion3/anomalies`.

Il backend riceve il messaggio e crea una notifica persistente. L'icona delle notifiche nell'header si aggiorna con il badge numerico. Il tecnico seleziona la notifica e accede al pannello notifiche (Figura 6.12).

Dall'elenco dei veicoli della sezione *Monitor* il tecnico seleziona `camion3` e accede alla dashboard telemetrica (Figura 6.13), dove può visualizzare i grafici storici dei parametri monitorati.

6.2.7 Fase 7 — Consultazione dei report (Tecnico)

Il tecnico accede alla sezione *Reports* per un'analisi più approfondita sull'operatività della flotta.

Selezionando il report **Operating Hours** (Figura 6.14), il tecnico visualizza la heatmap mensile che mostra i giorni di attività per ciascun veicolo. Cliccando su un giorno specifico, la vista esegue un drill-down sulle fasce orarie di funzionamento, consentendo di verificare in quale momento della giornata il veicolo era operativo.

Passando al report **Cumulative Hours** (Figura 6.15), il tecnico seleziona un intervallo temporale e visualizza l'istogramma di distribuzione delle ore totali di funzionamento dei veicoli, con curva cumulativa percentuale sovrapposta. Questa vista consente di identificare eventuali squilibri nell'utilizzo della flotta.

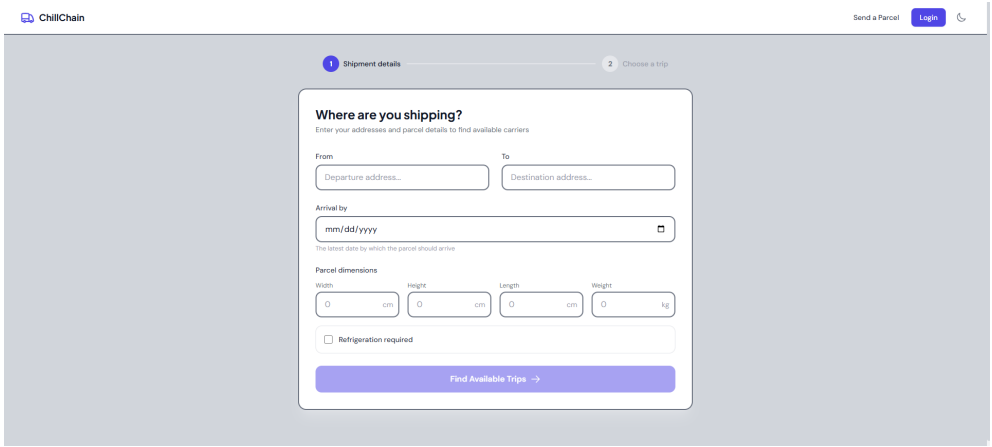

Figura 6.6: Form di ricerca tratte. Il cliente inserisce gli indirizzi di partenza e arrivo, le dimensioni e il peso del pacco, la necessità di refrigerazione e la data di arrivo massima tollerata.

Infine, il report **Alert Report** (Figura 6.16) mostra il conteggio delle anomalie per veicolo. Il tecnico può configurare la granularità temporale (anno, mese o giorno) e filtrare per singolo veicolo.

Per ciascun report, il tecnico ha la possibilità di esportare i dati in formato CSV tramite il pulsante *Export CSV*, per eventuali analisi esterne.

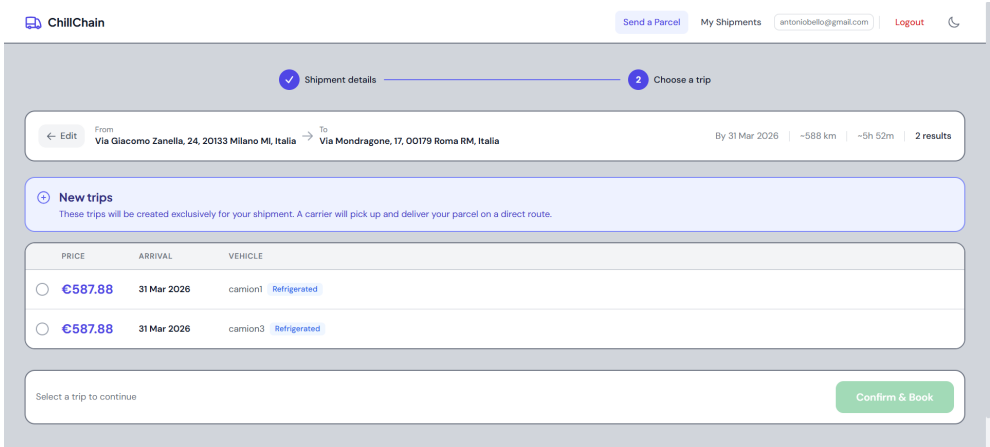

Figura 6.7: Risultati della ricerca tratte per il Cliente A. Sono visibili due veicoli disponibili con il percorso Milano–Roma, prezzo calcolato, distanza e durata stimata.

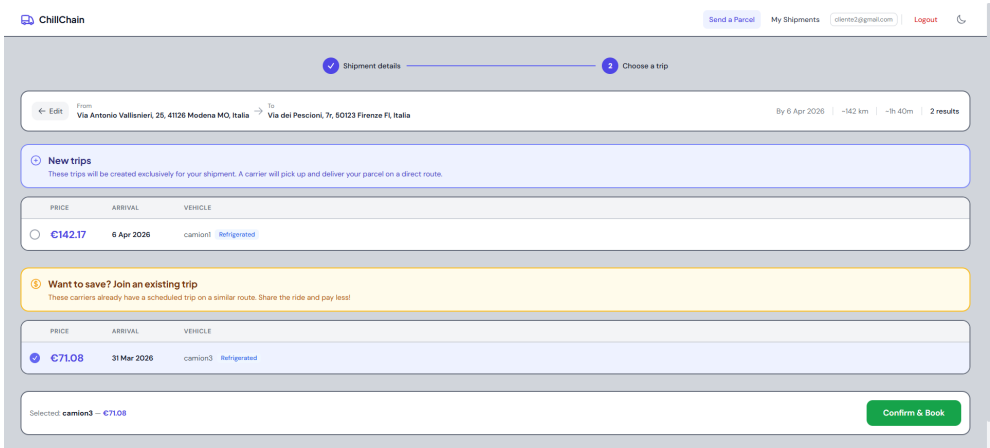

Figura 6.8: Risultati della ricerca tratte per il Cliente B. Oltre al veicolo `camion1` disponibile per un viaggio nuovo, compare `camion3` per un viaggio condiviso: il percorso Milano–Roma passa sufficientemente vicino a Modena e Firenze, la deviazione rientra nell'ora di tolleranza e il prezzo è scontato del 50%

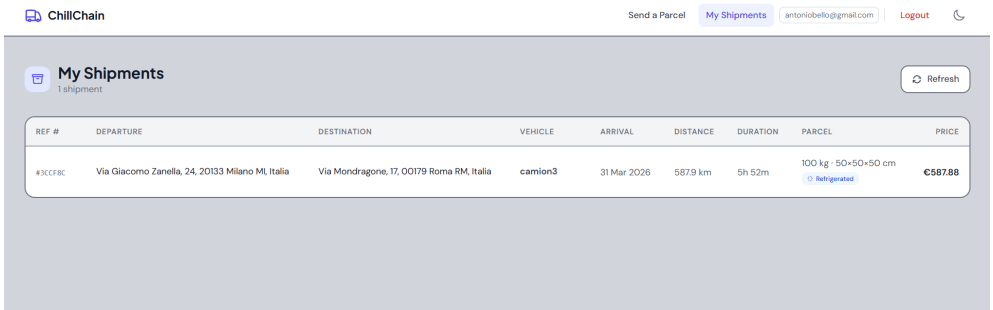

Figura 6.9: Pagina *My Shipments* del cliente. Sono elencate le spedizioni associate all'account autenticato, con indirizzi, dimensioni, peso, veicolo assegnato e prezzo.

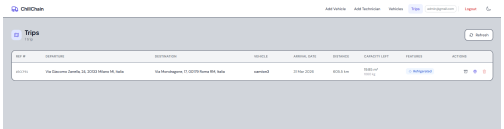

(a) Lista dei viaggi programmati.

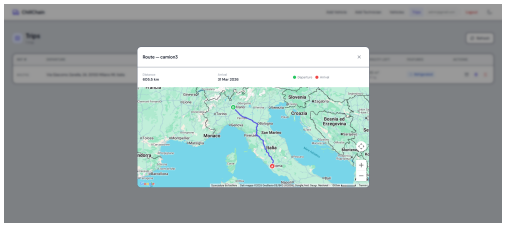

(b) Mappa del percorso del viaggio selezionato.

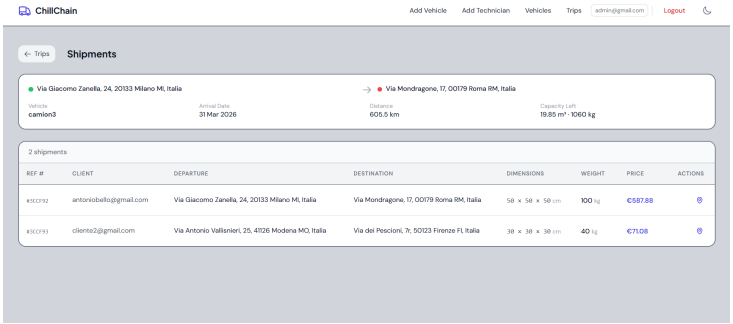

(c) Dettaglio del viaggio con elenco degli shipment associati.

Figura 6.10: Interfaccia di gestione dei viaggi programmati: lista dei viaggi disponibili, visualizzazione del percorso su mappa e dettaglio del viaggio selezionato con gli shipment associati.

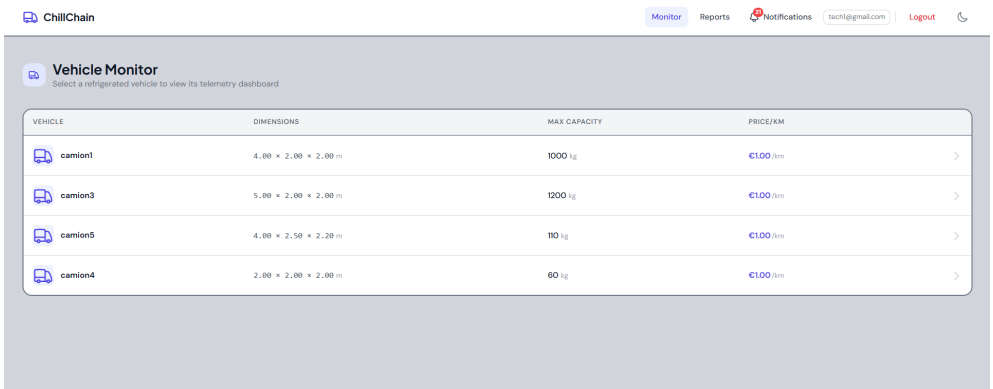

Figura 6.11: Elenco dei veicoli dotati di refrigerazione.

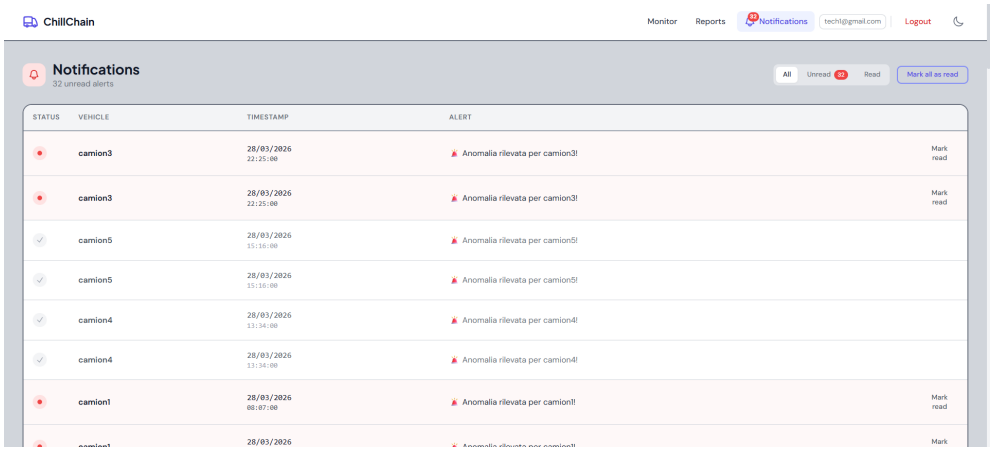

Figura 6.12: Pannello notifiche del tecnico. La notifica indica il veicolo interessato (`camion3`), il timestamp dell'allerta e il messaggio. Il badge nell'header mostra il conteggio delle notifiche non lette.

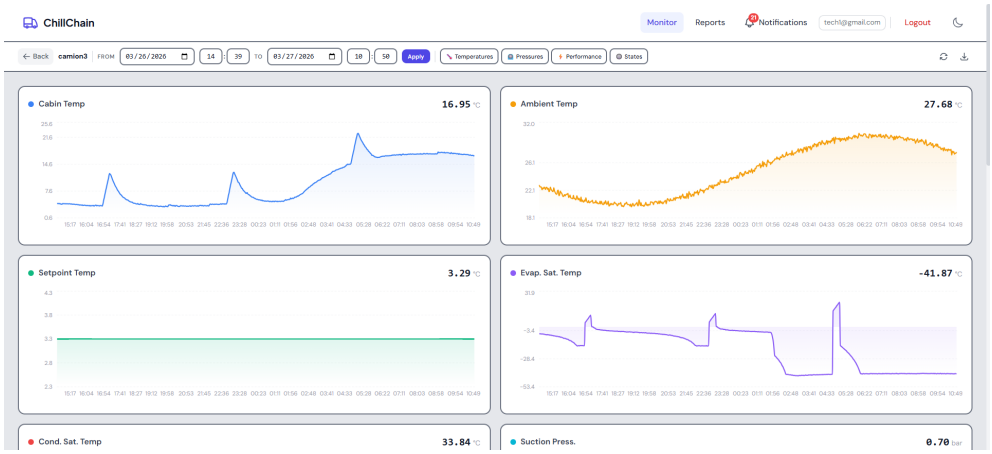

Figura 6.13: Dashboard telemetrica del veicolo `camion3`.

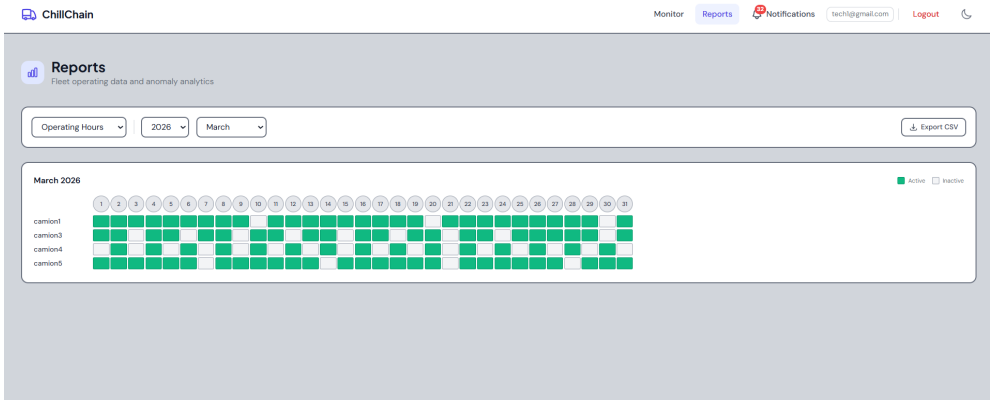

(a) Vista mensile: heatmap giorni di attività per veicolo.

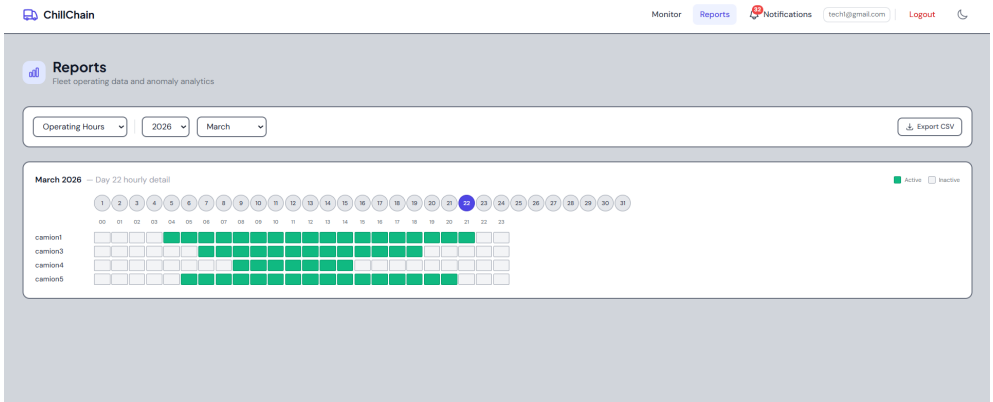

(b) Drill-down giornaliero: fasce orarie di funzionamento.

Figura 6.14: Report *Operating Hours*. (a) La heatmap mensile evidenzia i giorni in cui ciascun veicolo era operativo. (b) Selezionando un giorno, la griglia si trasforma mostrando il dettaglio orario.

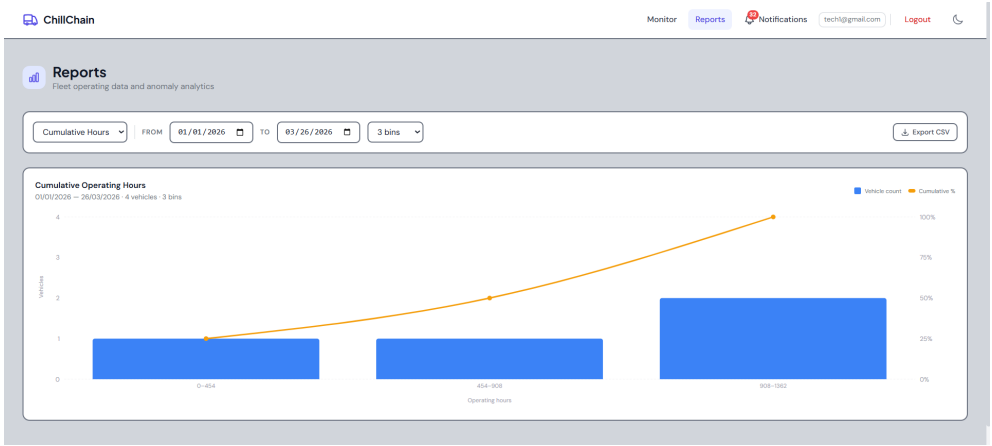

Figura 6.15: Report *Cumulative Hours*. L'istogramma mostra la distribuzione delle ore totali di funzionamento dei veicoli nell'intervallo selezionato, con curva cumulativa percentuale sovrapposta.

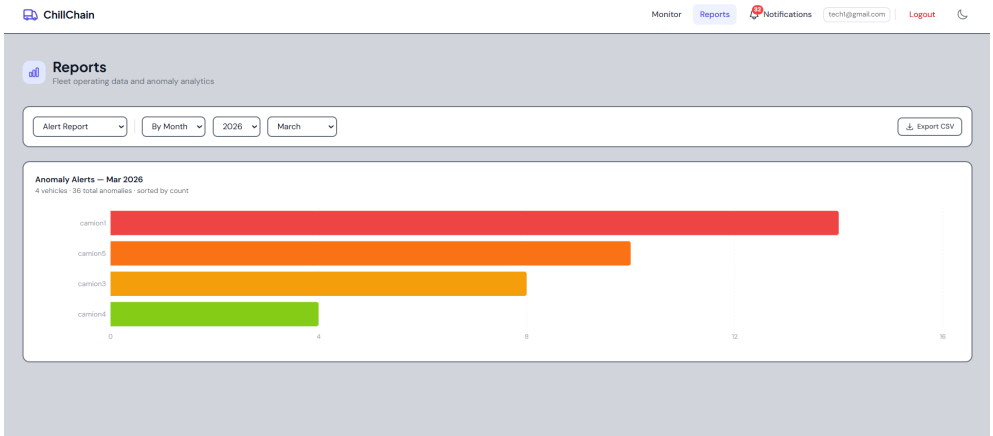

Figura 6.16: Report *Alert Report*. Il grafico mostra il conteggio delle anomalie per veicolo con granularità temporale configurabile.

Capitolo 7

Conclusioni e Sviluppi Futuri

7.1 Conclusioni

L'obiettivo di questo lavoro era la progettazione e l'implementazione di una piattaforma IoT integrata per il trasporto refrigerato condiviso, capace di unire in un unico sistema due funzionalità tradizionalmente separate: un marketplace per il matching tra domanda e offerta di spedizioni e un sistema di monitoraggio delle condizioni del vano di refrigerazione dei veicoli con rilevazione automatica delle anomalie.

7.2 Sviluppi futuri

Nonostante i risultati ottenuti, il lavoro presenta margini di miglioramento che possono essere affrontati in sviluppi successivi.

7.2.1 Ottimizzazione temporale e scheduling attivo

L'attuale algoritmo di matching tra spedizioni e viaggi opera prevalentemente sulla dimensione spaziale, valutando la prossimità geografica tra i punti di ritiro/consegna e la polyline del percorso. La dimensione temporale, pur presente sotto forma di data di scadenza della spedizione, non viene sfruttata in modo strutturato per guidare la pianificazione dei viaggi. Un sistema più maturo potrebbe integrare le finestre di disponibilità dei trasportatori, i periodi di inattività dei veicoli e i vincoli temporali delle spedizioni in un unico modello di ottimizzazione.

7.2.2 Scalabilità su piattaforme cloud

L'attuale architettura è validata in ambiente locale tramite Docker Compose. Per un utilizzo in produzione sarebbe necessario il deployment su piattaforme cloud come AWS o Azure, sfruttando servizi gestiti quali container orchestration (ECS/EKS), database managed (MongoDB Atlas), e broker MQTT gestiti (AWS IoT Core). Questo garantirebbe alta disponibilità, auto-scaling in funzione del carico e ridondanza geografica.

7.2.3 Miglioramento della sensibilità dell'anomaly detection

Il modello LSTM autoencoder attuale opera sulle 15 feature grezze del dataset di telemetria refrigerata. Anomalie sottili come il *sensor drift*, in cui un sensore si degrada progressivamente nel tempo senza generare un errore di ricostruzione elevato su singole osservazioni, risultano difficili da rilevare con questo approccio.

Un miglioramento consiste nell'estrazione di feature derivate da fornire in input al modello.

7.2.4 Indicizzazione spaziale con PostGIS

Il calcolo della distanza punto-polyline, utilizzato per determinare la compatibilità tra un punto di ritiro/consegna e un percorso esistente, avviene attualmente con una scansione lineare $O(n)$ su tutti i segmenti della polyline decodificata. Questa complessità diventa un collo di bottiglia all'aumentare del numero di viaggi e della lunghezza dei percorsi.

L'adozione di PostgreSQL con l'estensione PostGIS consentirebbe di sfruttare l'indicizzazione spaziale tramite R-tree: la funzione `ST_Distance` opera su geometrie indicizzate con complessità $O(\log n)$, riducendo drasticamente il tempo di ricerca. Inoltre, PostGIS offre nativamente operazioni come il buffer spaziale e l'intersezione tra geometrie.

7.2.5 Sistema di notifiche push per il tecnico

Il sistema attuale di notifiche per anomalie è consultabile esclusivamente tramite la dashboard web: il tecnico deve accedere alla piattaforma per verificare la presenza di nuovi alert. In un contesto operativo reale, le anomalie della catena del freddo richiedono interventi tempestivi. L'integrazione di canali di notifica push, tramite email (SMTP o servizi come SendGrid) e notifiche

mobile (Firebase Cloud Messaging), garantirebbe che il tecnico venga avvisato immediatamente al verificarsi di un'anomalia, indipendentemente dal fatto che stia consultando la dashboard in quel momento.

Bibliografia

[1] Carrier Global Corporation. *Carrier Lynx: Digital Platform for the Connected Cold Chain*. https://www.carrier.com/carrier/en/worldwide/cold-chain/connected-cold-chain/lynx/. Accessed: 2026-03-06. 2024.

[2] Flock Freight. *FlockDirect® Shared Truckload*. 2024. URL: https://www.flockfreight.com (visitato il 24/02/2025).

[3] Di Hu et al. «Anomaly Detection of Power Plant Equipment Using Long Short-Term Memory Based Autoencoder Neural Network». In: *Sensors* 20.21 (2020), p. 6164. DOI: 10.3390/s20216164. URL: https://www.mdpi.com/1424-8220/20/21/6164.

[4] Pankaj Malhotra et al. «LSTM-based Encoder-Decoder for Multi-sensor Anomaly Detection». In: *arXiv preprint arXiv:1607.00148* (2016). DOI: 10.48550/arXiv.1607.00148. URL: https://arxiv.org/abs/1607.00148.

[5] Mikhail Samoilov. *Simulated Refrigerator Fault Diagnosis Dataset*. 2024. URL: https://www.kaggle.com/datasets/samoilovmikhail/simulated-refrigerator-fault-diagnosis-dataset (visitato il 24/02/2025).

[6] Yuanyuan Wei et al. «LSTM-Autoencoder Based Anomaly Detection for Indoor Air Quality Time Series Data». In: *arXiv preprint arXiv:2204.06701* (2022). DOI: 10.48550/arXiv.2204.06701. URL: https://arxiv.org/abs/2204.06701.